BALUDiK

Jeux de piste numériques

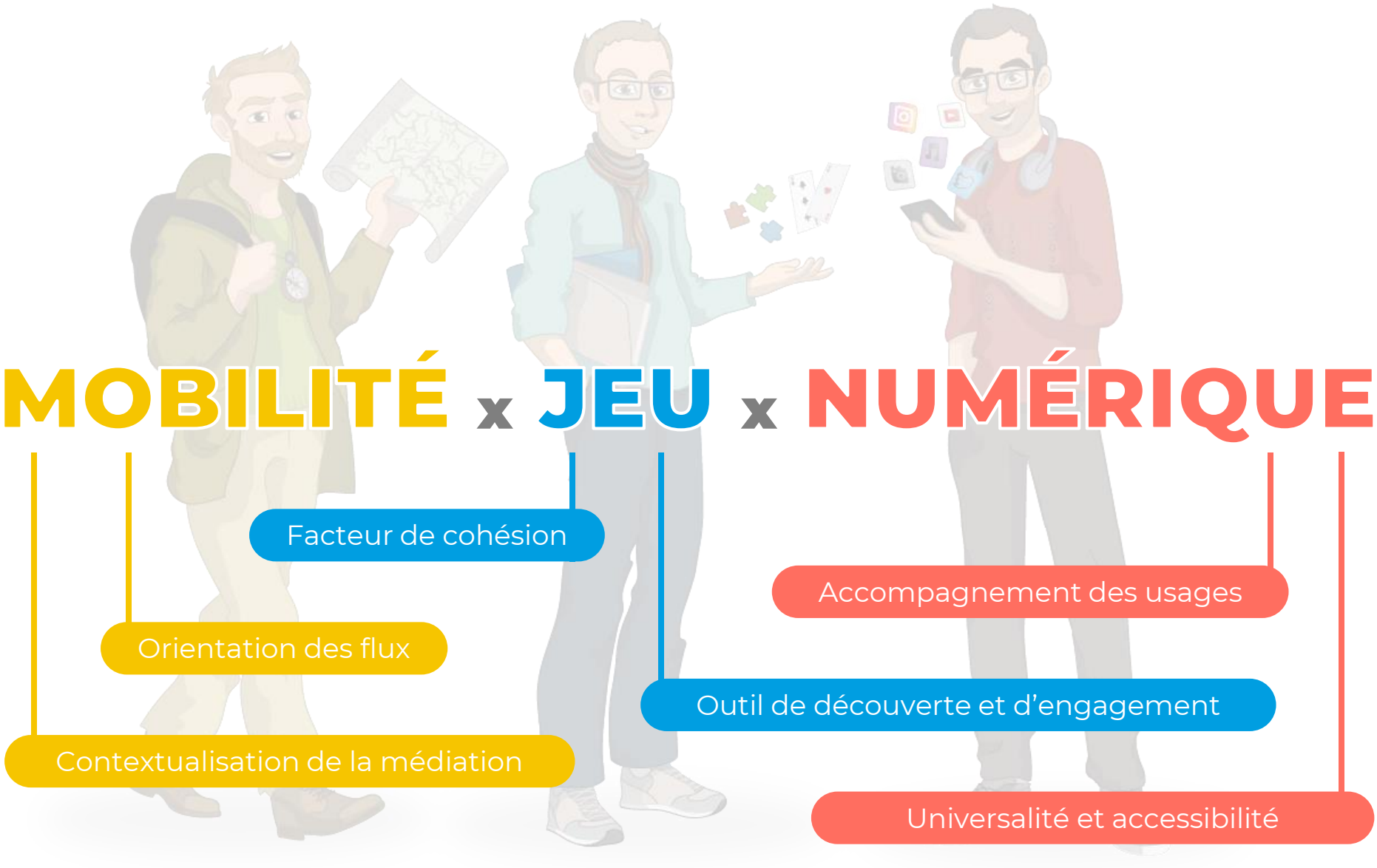
MOBILITÉ x JEU x NUMÉRIQUE
Facteur de cohésion
Orientation des flux
Contextualisation de la médiation
Accompagnement des usages
Outil de découverte et d'engagement
Universalité et accessibilité

L'APPLICATION BALUDIK, UN PORTAIL COMPLET

LE CONCEPT DE BALUDIK

La solution Baludik s'appuie sur une application portail à destination des utilisateurs finaux.

Gratuite au téléchargement, elle permet d'accéder à un catalogue multithématique de centaines de parcours, jeux de piste, chasses au trésor...

Ces parcours sont proposés par des structures du tourisme, de la culture, de l'événementiel qui peuvent s'appuyer sur les compétences de l'équipe Baludik non seulement pour la réalisation technique mais également en matière de scénarisation, Game Design et création graphique.

GRATUITE, UNIVERSELLE ET RESPONSABLE

- Gratuite au téléchargement sur Android et iOS
- Compatibilité maximale avec les appareils du marché
- Intuitivité de navigation
- Accessibilité et empreinte énergétique
- Respect du cadre réglementaire RGPD
- Fonctionnelle en zone blanche
- Disponible en plusieurs langues
- Compatible en intérieur comme en extérieur

COMMENT ÇA MARCHE ?

1 LE JOUEUR TÉLÉCHARGE GRATUITEMENT L'APPLICATION BALUDIK

DISPONIBLE SUR Google Play

Télécharger dans l'App Store

2 IL VISUALISE LES PARCOURS DISPONIBLES

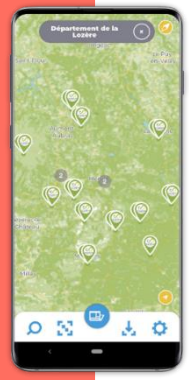

Au lancement, une carte interactive présente les jeux et parcours géolocalisés à proximité de son emplacement.

Il peut également accéder à un parcours ou à l'ensemble des parcours proposés par une destination en scannant le QR Code associé.

3 IL SÉLECTIONNE LE PARCOURS DE SON CHOIX

En cliquant sur le marqueur, il découvre les informations générales et le scénario dans lequel il va s'engager.

Il télécharge les contenus : il ne dépend plus de la couverture réseau pour pouvoir vivre l'expérience, même en zone blanche.

4 C'EST PARTI !

LE JOUEUR SE VOIT CONFIER POUR MISSION DE DÉCOUVRIR ET DÉBLOQUER TOUTES LES ÉTAPES DU JEU DE PISTE POUR POUVOIR ACCÉDER À LA CONCLUSION, AVEC POUR CHAQUE ÉTAPE UN DÉROULEMENT EN 3 PHASES :

JE M'AIDE DES INDICES

Pour chaque mission, je suis aidé de 1 à 4 indices ou consignes.

Selon la nature de la mission à accomplir, ces indices peuvent prendre plusieurs formes : aide à l'orientation ou à la géolocalisation, détail d'une image, énigme à décoder...

J'ACCOMPLIS LA MISSION

Si l'étape m'invite à trouver le lieu à rejoindre, le simple fait de s'y rendre valide ma mission !

Je peux aussi être amené à répondre à une question, à compléter un mini-jeu (puzzle, coloriage, memory...)
Parfois il peut s'agir d'interagir avec mon environnement en utilisant la reconnaissance d'image en réalité augmentée...

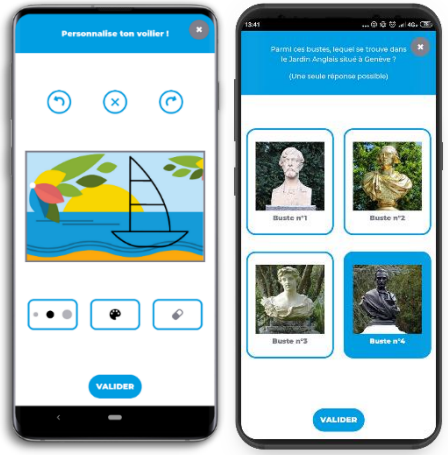

JE DÉBLOQUE LES CONTENUS

Le fait de valider une mission me permet de découvrir du contenu informatif (texte, images, audio...)
Des fonctionnalités interactives comme le « panorama augmenté » , une véritable table d'orientation en réalité augmentée, sont également proposées.

Je peux ensuite accéder à ma prochaine mission et donc continuer mon jeu de piste jusqu'à la récompense finale !

NATURAL AND CULTURAL LANDSCAPES	Support de médiation et valorisation
HERITAGE, CULTURE AND ARTS	Support de médiation et valorisation
NATURE AND WILDLIFE	Support de médiation et valorisation
AGRICULTURE	Support de médiation et valorisation
SUSTAINABLE TOURISM	Acteur de cette ligne directrice
TRANSPORT AND CONNECTIVITY	Expérience augmentée
RESTORATION AND REGENERATION	Relais de communication et sensibilisation
URBAN STANDARDS AND ARCHITECTURE GUIDELINES	Relais de communication et sensibilisation
PROMOTE ECONOMIC AND SOCIAL DEVELOPMENT	« Promesse RSE » de Baludik
SUPPORTING INFRASTRUCTURE	Relais de communication et sensibilisation
SECURITY	N/A

Musées de Bruxelles
Valorisation des collections

Ile de la Réunion – OT de l'Ouest
Médiation numérique au sein du Parc National du Mafate

Transdev
Promotion et sensibilisation autour de la mobilité

Port Nantes – Saint-Nazaire
Amélioration de la perception citoyenne autour d'une infrastructure industrielle

Département des Hauts-de-Seine
Fédération des lieux culturels
Incitation à la visite des musées

Center Parcs
Expérience ludique au sein d'un Resort

Université de la Sorbonne
Valorisation de fouilles archéologiques dans le sud marocain

Station de Val Thorens
Animation ludique événementielle à destination des familles

Conservatoire botanique national de Brest
Education à l'environnement autour de la faune et de la flore

Agence de l'eau Rhin-Meuse
Valorisation de la gestion de l'eau à l'échelle d'un bassin versant

UN DISPOSITIF A PLUSIEURS DIMENSIONS :

THÉMATIQUE	CIBLE	FORMAT	MODE DE MOBILITÉ
Patrimoine	Tourisme famille	Jeu permanent	A pied
Faune et flore	Tourisme adulte	Chasse au trésor	En voiture
Culture	Aventure	Audioguide	Statique
Art de vivre	Business	Événementiel	Distant
Innovation durable	Scolaires	Animation	
Activités	Population locale	Séminaire	...

EXEMPLE DE DISPOSITIF DE 6 PARCOURS REALISABLE RAPIDEMENT :

1. JEU DE PISTE FAMILIAL « LAND ART » À WADI AL FANN
2. ENQUÊTE FAMILIALE « ARCHÉOLOGIE » À AL ULA OLD TOWN
3. AUDIOGUIDE FAMILIAL « CULTURE » À HEGRA
4. JEU DE PISTE FAMILIAL « ART DE VIVRE » À HEGRA
5. JEU DE PISTE BUSINESS « PROJECTION 2035 » À AL ULA
6. CHASSE AUX POINTS D'INTÉRÊT PATRIMONIAUX MULTI-SITES

SHARING
GOODWILL
COHESION
PERFORMANCE

BALUDiK

2 RUE ALFRED KASTLER 44300 NANTES
09 86 68 60 00
CONTACT@BALUDIK.FR